「童亮自由玩！」社區地圖
Padlet 使用指南與圖例卡

Padlet 社區地圖進入方法 (裝置需連接至網際網路)

找到「相機」並打開程序



1. 掃描二維碼進入「童亮自由玩！」社區地圖選項
   （或使用二維碼下的網址進入）

或使用：qr.link/KCA6OT

2. 選擇討論組別的所屬地區進入社區地圖

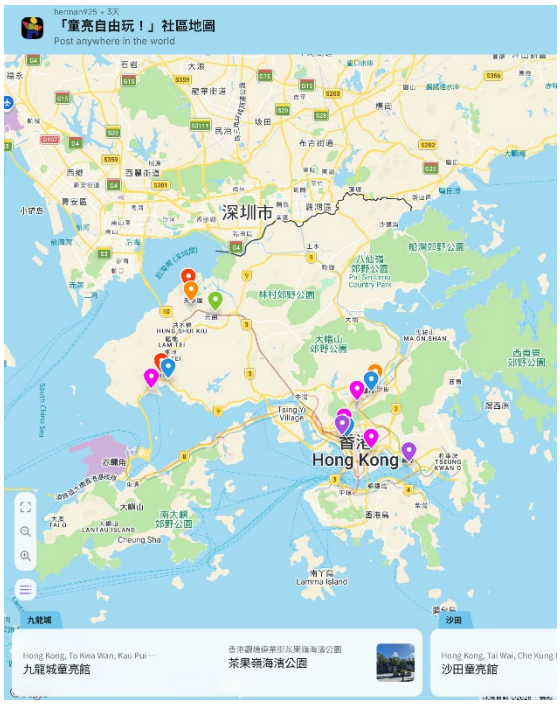

Padlet 使用指南

1. 點擊「+」號新增地點

2. 輸入要新增的地點並點選正確地址
3. 填寫推薦原因（選填）並設定地方類別
(注意：請先勿發佈！)

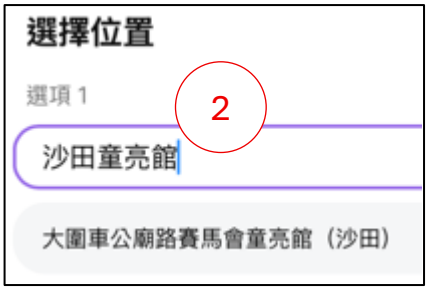

4. 下方找到增加多媒體圖示，點選你想要新增的內容（推薦「連結」、「圖像」）
5. 完成後點擊「發佈」則可將推薦地點發佈到社區地圖上



示範地點一覽（社區資源示例）

地點	地區	類別	推薦原因重點
元朗公園 (大橋路)	元朗	戶外	廣闊無圍欄草坪讓孩子自訂規則，噴泉廣場引發自發性水玩
天水圍公園 (天瑞路)	元朗	戶外	迷宮/洞穴引發探索欲，香味植物刺激感官好奇心
兆麟體育館兒童遊戲室	屯門	室內	攀石牆讓孩子自己決定爬多高，室內不受天氣干擾
屯門公園共融遊樂場	屯門	戶外	無固定玩法水沙設計；傷健兒童自然同場互動
深水埗公園兒童遊樂場	深水埗	戶外	高滑梯讓孩子自主評估風險、克服恐懼
北河街體育館兒童遊戲室	深水埗	室內	安靜環境讓孩子深度投入，適合需要低刺激環境的孩子
車公廟體育館兒童遊戲室	沙田	室內	孩子自主選擇活動；平台花園提供半戶外靜態遊玩空間
沙田公園 (源禾路)	沙田	戶外	石山、城堡、迷宮是沒有劇本的空間，孩子自然發展角色扮演
茶果嶺海濱公園 (偉業街)	觀塘	戶外	樹屋繩網讓孩子面對高度、測試膽量

步驟 1：如何在 Padlet 標記地點？

1. 標題：填寫地點名稱（例如：九龍公園）
2. 相片：上載或搜尋該地點的相片
3. 區段：選擇該地點所屬的地區（如：九龍城、沙田等）
4. 地方類別（必填）：童亮館、室內遊樂設施、戶外遊樂設施、公共空間、圖書館、其他

步驟 2：如何標記「推薦原因 / 遊戲價值」？

根據地點最吸引人的遊戲價值，更改貼文的顏色（如圖示）。

白色 = 童亮館
只限用於標記各區的童亮館。

紅色 = 社交與共融 (Social & Inclusive)
小朋友在這裡自然地找到玩伴、主動加入遊戲、一起協商玩法——不需大人安排。

黃色 = 探索與想像 (Exploration & Imagination)
環境本身就是玩具——小朋友可以自己發明玩法、改變規則、把地方變成自己的故事場景。

綠色 = 活力與大肌肉 (Active & Physical)
身體是最好的玩具——這裡給小朋友空間盡情奔跑、攀爬、跳躍，由自己決定活動量和節奏。

藍色 = 寧靜與專注 (Quiet & Focused)
這裡讓小朋友按自己步伐深度投入：拼圖、共讀、感官探索，家長也可以放鬆陪伴。

紫色 = 刺激與挑戰 (Thrill & Challenge)
這裡讓孩子在安全環境下體驗冒險、克服恐懼、感受「我做到了！」的喜悅。

參考地點一覽（九大社區資源示例）

地點	地區	類別	顏色	推薦原因重點
元朗公園 (大橋路)	元朗	戶外		廣闊無圍欄草坪讓孩子自訂規則，噴泉廣場引發自發性水玩
天水圍公園 (天瑞路)	元朗	戶外		迷宮/洞穴引發探索欲，香味植物刺激感官好奇心
兆麟體育館兒童遊戲室	屯門	室內		攀石牆讓孩子自己決定爬多高，室內不受天氣干擾
屯門公園共融遊樂場	屯門	戶外		無固定玩法水沙設計；傷健兒童自然同場互動
深水埗公園兒童遊樂場	深水埗	戶外		高滑梯讓孩子自主評估風險、克服恐懼
北河街體育館兒童遊戲室	深水埗	室內		安靜環境讓孩子深度投入，適合需要低刺激環境的孩子
車公廟體育館兒童遊戲室	沙田	室內		孩子自主選擇活動；平台花園提供半戶外靜態遊玩空間
沙田公園 (源禾路)	沙田	戶外		石山、城堡、迷宮是沒有劇本的空間，孩子自然發展角色扮演
茶果嶺海濱公園 (偉業街)	觀塘	戶外		樹屋繩網讓孩子面對高度、測試膽量